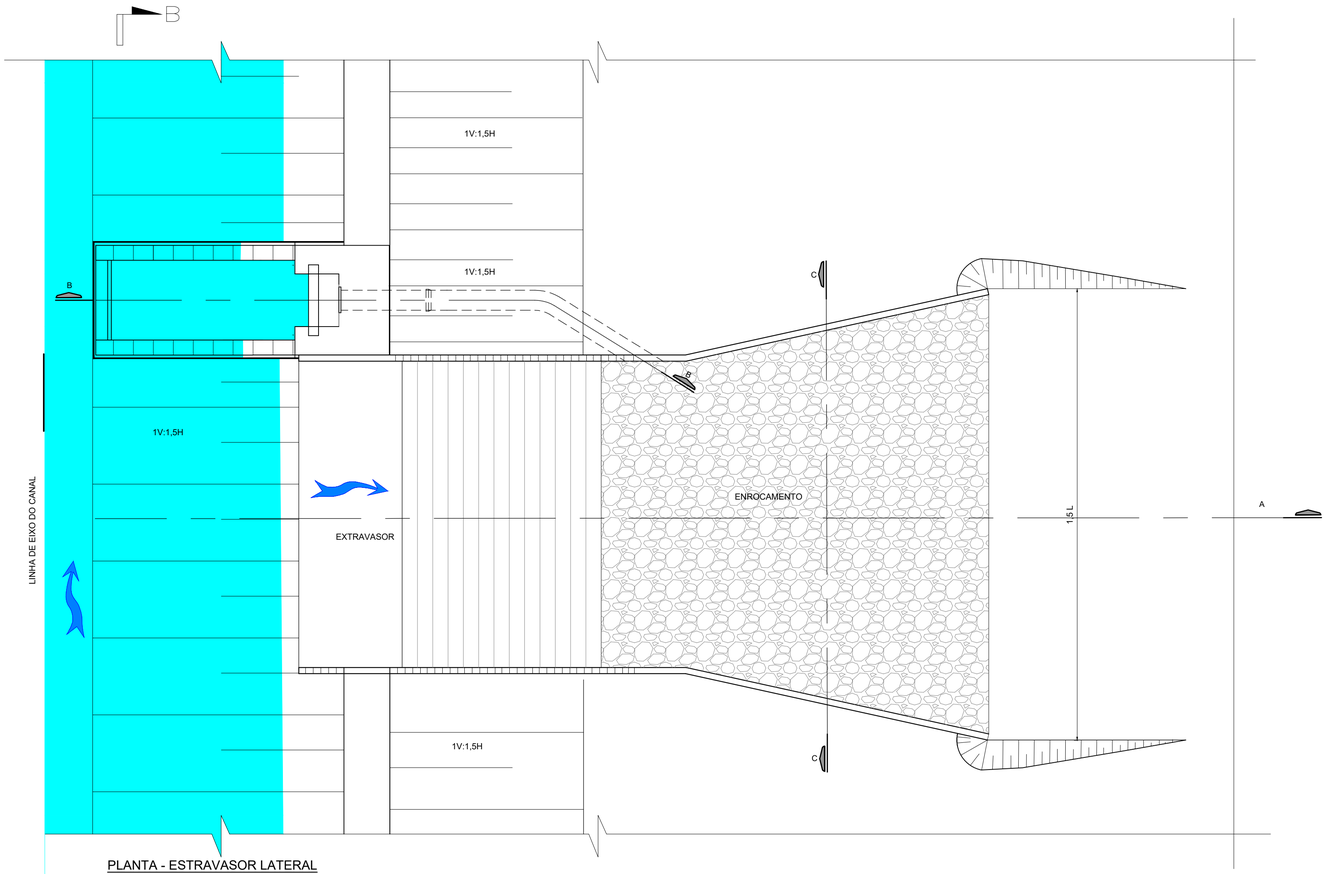
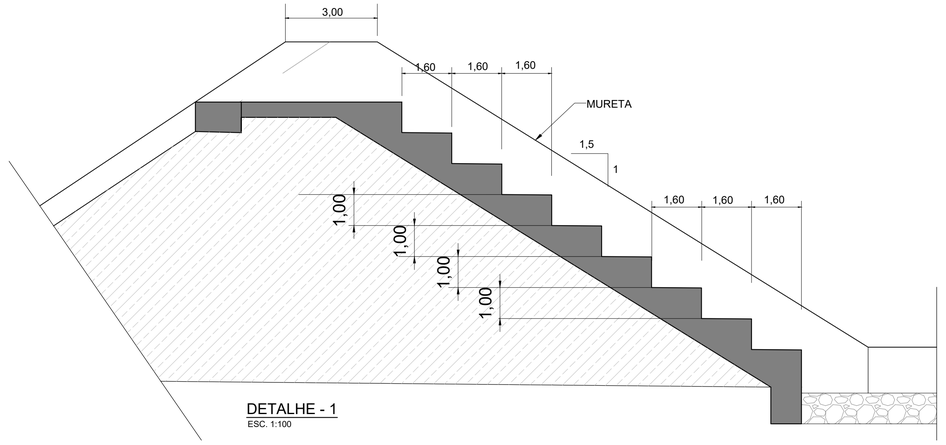
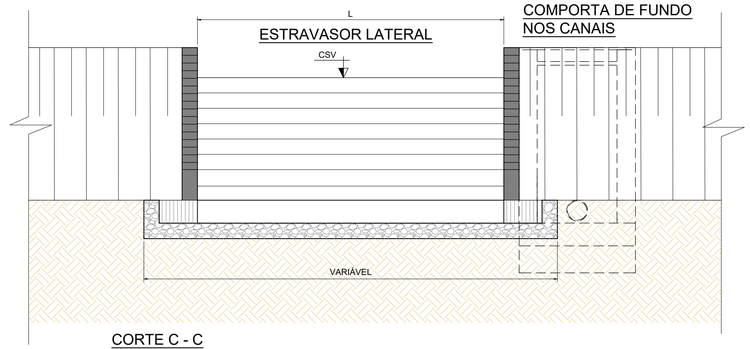


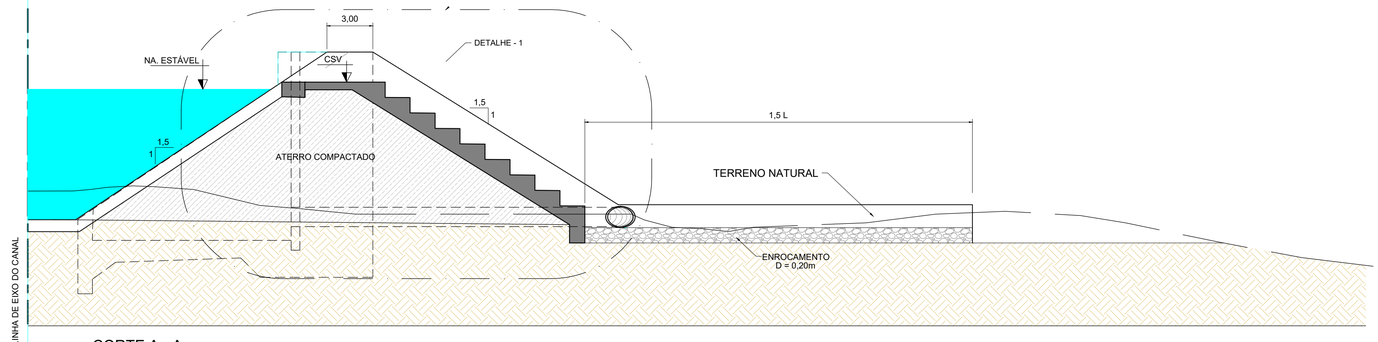
PLANTA - ESTRAVASOR LATERAL
ESC.: 1:200



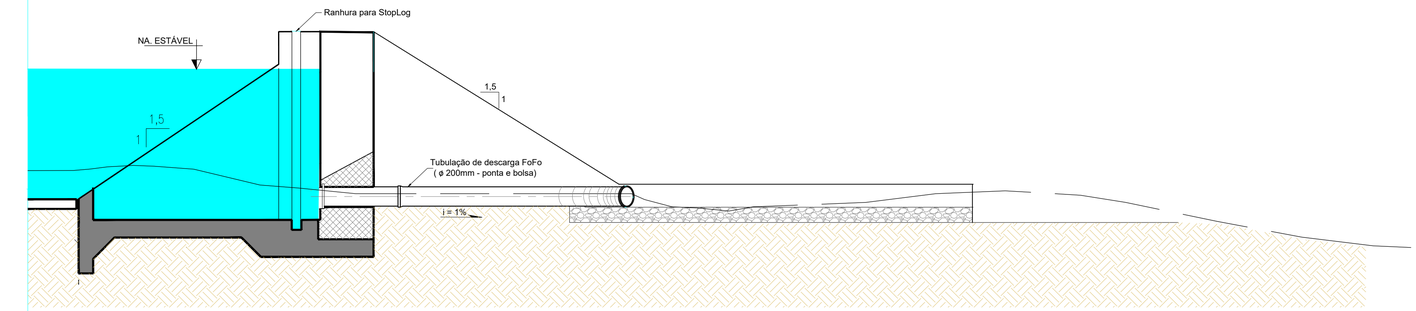
DETALHE - 1
ESC. 1:100



CORTE C - C
ESC. 1:200



CORTE A - A
ESC. 1:200



CORTE B - B -COMPORTA DE FUNDO NOS CANAIS
ESC. 1:200

Etapa	Obra	Trecho	Posição do extravasor	Margem do canal	Vazão no canal	NA estático	Cota da soleira do extravasor (CSV)	% da vazão do canal	Ω extravasor	Comprimento do extravasor (L)	Lâmina vertente (h)	Cota da berma
			(km+m)	(E/D)	(m³/s)	(m)	(m)		(m³/s)	(m)	(m)	(m)
3	EX-1	CS19-Trecho 2	4+200	D	3,81	475,05	475,10	50%	1,91	20,50	0,15	475,35
	EX-2	CS19-Trecho 3	9+400	D	2,74	474,16	474,21	50%	1,37	14,80	0,15	474,41
	EX-3	CS19-Trecho 4	10+750	E	2,01	473,31	473,36	50%	1,00	10,80	0,15	473,56
	EX-4	CS19-Trecho 5	19+500	D	2,01	472,47	472,52	50%	1,00	10,80	0,15	472,72
	EX-5	CT1-CS19-Trecho 1	3+950	D	1,16	474,40	474,54	50%	0,58	6,20	0,15	474,74
	EX-6	CT1-CS19-Trecho 2	10+500	D	0,38	473,01	473,06	100%	0,38	4,10	0,15	473,21
3	EX-1	CS21	1+350	E	6,59	478,22	478,27	35%	2,31	24,90	0,15	478,52
	EX-2	CS21a - Trecho 1	3+300	D	4,73	479,98	480,03	35%	1,66	17,80	0,15	480,28
	EX-3	CS21a - Trecho 2	7+900	D	3,93	479,28	479,33	50%	1,97	21,20	0,15	479,53
	EX-4	CS21a - Trecho 3.1	11+700	E	2,81	463,76	463,81	50%	1,41	15,10	0,15	464,01
	EX-5	CS21a - Trecho 4	15+900	D	1,62	463,12	463,17	50%	0,81	8,70	0,15	463,37
	EX-6	CS21a - Trecho 5	0+021	D	1,62	462,18	462,23	50%	0,81	8,70	0,15	462,43
	CT2-S21		2+200	D	0,89	479,93	479,98	50%	0,45	4,80	0,15	480,18
4	EX-1	CP3 - Trecho 2	5+500	E	8,74	478,87	478,92	35%	3,06	33,00	0,15	479,17
	EX-2	CP3 - Trecho 3	9+750	D	4,42	477,83	477,88	35%	1,55	16,70	0,15	478,13
	EX-3	CP3a - Trecho 1	2+700	D	3,43	480,95	481,00	50%	1,71	18,50	0,15	481,20
	EX-4	CP3a - Trecho 2	7+500	D	2,13	479,95	480,00	50%	1,06	11,50	0,15	480,20
	EX-5	CP3b - Trecho 1	1+400	D	1,53	486,04	486,09	50%	0,76	8,30	0,15	486,29
4	EX-6	CS23	1+750	E	0,28	477,14	477,19	100%	0,28	3,10	0,15	477,34
	EX-7	CS25 - Trecho 1	3+550	E	2,68	480,42	480,47	50%	1,34	14,40	0,15	480,67
	EX-8	CS25 - Trecho 2	4+800	D	1,14	479,42	479,47	50%	0,57	6,20	0,15	479,67
	EX-9	CS27	2+400	E	0,54	480,12	480,17	50%	0,27	2,90	0,15	480,32

NOTAS:

1 - MEDIDAS, COORDENADAS E ELEVAÇÕES EM METRO.

Revisão	Data	Descrição	Elab.	Verif.	Aprov.	Aut.
1	06/07/26	REPOSICIONAMENTO DAS ESTRUTURAS	NP	AHL	EDK	
0	19/11/25	EMISSÃO INICIAL	NP	AHL	EDK	

REVISÕES - 1

AS ESTRUTURAS INDICADAS FORAM REPOSICIONADAS EM DECORRÊNCIA DA ALTERAÇÃO DO PERÍMETRO IRRIGÁVEL DA ETAPA 3, CONFORME SOLICITAÇÕES FEITAS APÓS CONSULTA PÚBLICA. OS PARÂMETROS DE PROJETO PERMANECEM CONFORME ESTABELECIDO NA VERSÃO ANTERIOR DO ESTUDO.

FUNDO DE DESENVOLVIMENTO DA INFRAESTRUTURA REGIONAL SUSTENTÁVEL - FDIRS

ESTRUTURAÇÃO DE PROJETO DE CONCESSÃO DO PERÍMETRO IRRIGADO DO JAÍBA (ETAPAS 3 E 4)

ANTEPROJETO

EXTRAVASOR LATERAL E COMPORTA DE FUNDO

PROJETO TÍPICO
PLANTA BAIXA, CORTES E TABELA

Finalidade de Emissão: 1 Para Informação | 2 Para Comentários | Para Aprovação | 4 Para Execução | 5 Como Construído | 6 Para Utilização | 7 Para Providências

Moysés & Pires Consultoria em Engenharia | ENGECORPS Consultoria | AMAM | Plena Consultoria e Projetos

Data:
Elaboração:
Verificação:
Escala: INDICADA
Aprovação
Autorização
Referência:
Revisão: 1
Desenho nº JA-DS-HI-0002