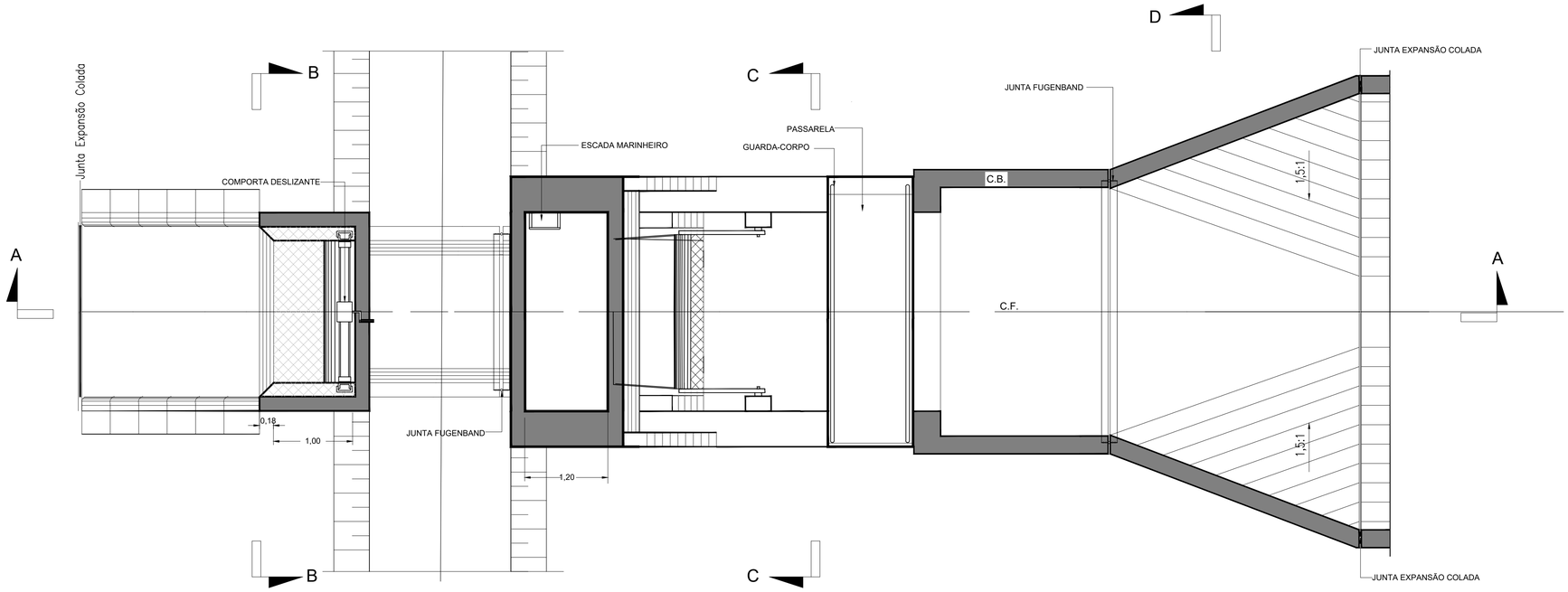
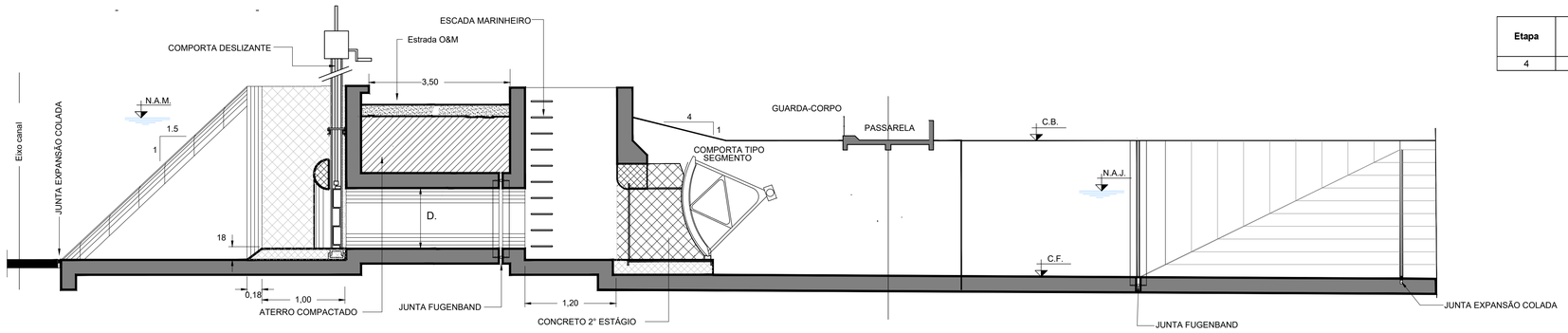
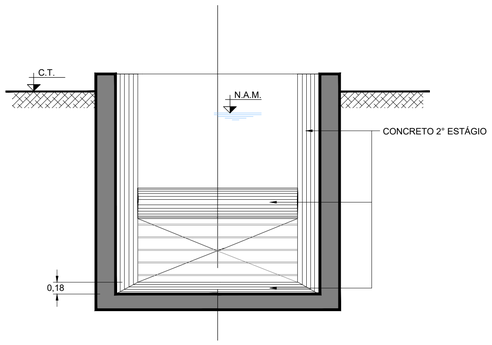


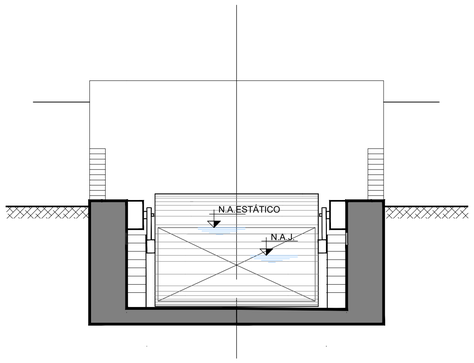
PLANTA BAIXA



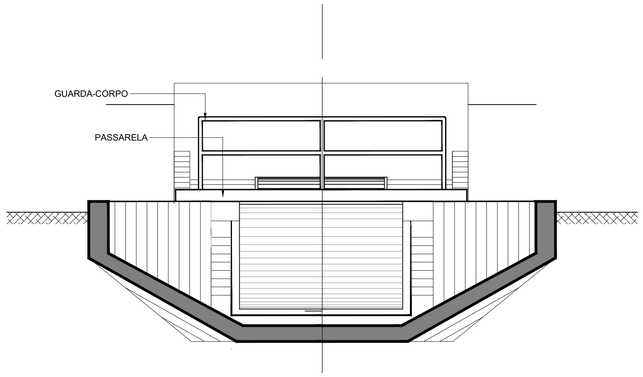
CORTE A - A



CORTE B - B



CORTE C - C



CORTE D - D

Etapa	Canal	Localização / Estaca	Derivação	Cota de fundo (C.F.)	N.A. estático	N.A. dinâmico (N.A.M)	N.A. dinâmico (N.A.J)	Cota terreno (C.T.)	Cota da berma (C.B.)	D
		(km)		(m)	(m)	(m)	(m)	(m)	(m)	(m)
4	CP3	1+950,00	CS-23	476,61	479,10	2,30	478,83	477,00	479,12	0,50

NOTAS:

1 - MEDIDAS, COORDENADAS E ELEVAÇÕES EM METRO.

Revisão	Data	Descrição	Elab.	Verif.	Aprov.	Aut.
1	04/12/25	REVISÃO DAS VAZÕES DE PROJETO	NP	AHL	EDK	
0	19/11/25	EMISSÃO INICIAL	NP	AHL	EDK	

FUNDO DE DESENVOLVIMENTO DA INFRAESTRUTURA REGIONAL SUSTENTÁVEL - FDIRS

ESTRUTURAÇÃO DE PROJETO DE CONCESSÃO DO PERÍMETRO IRRIGADO DO JAÍBA (ETAPAS 3 E 4)

ANTEPROJETO

DERIVAÇÃO COM COMPORTA
PLANTA BAIXA
CORTES E TABELA

Finalidade de Emissão	1 Para Informação	2 Para Comentários	Para Aprovação	4 Para Execução	5 Como Construído	6 Para Utilização	7 Para Providências

Moysés & Pires Engenharia e Meio Ambiente | ENGECORPS Engenharia | AHA Engenharia | Plena Consultoria e Projetos

Data:	Elaboração:		Verificação:
Escala: sem escala	Aprovação	-	Autorização -
Referência:	Revisão: 1	Desenho nº JA-DS-HI-0007	