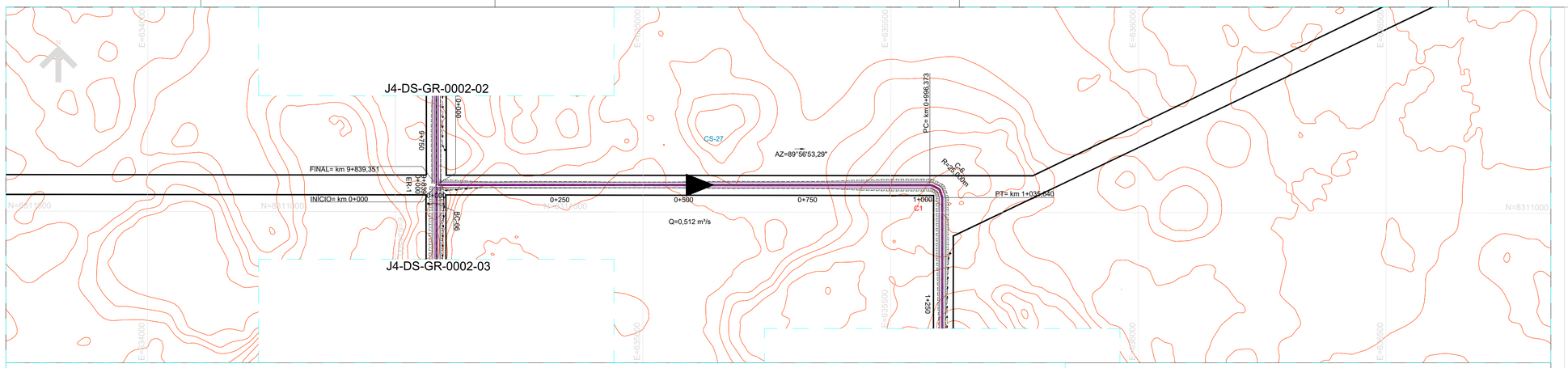
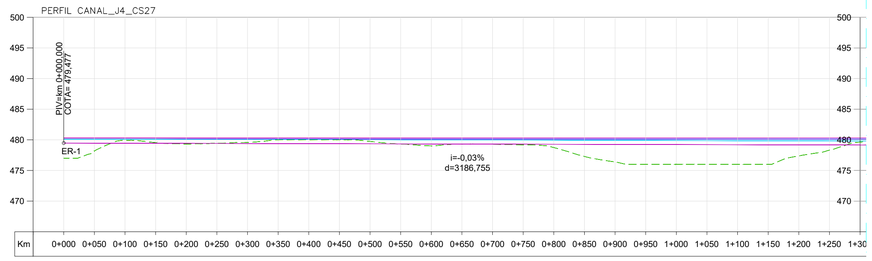
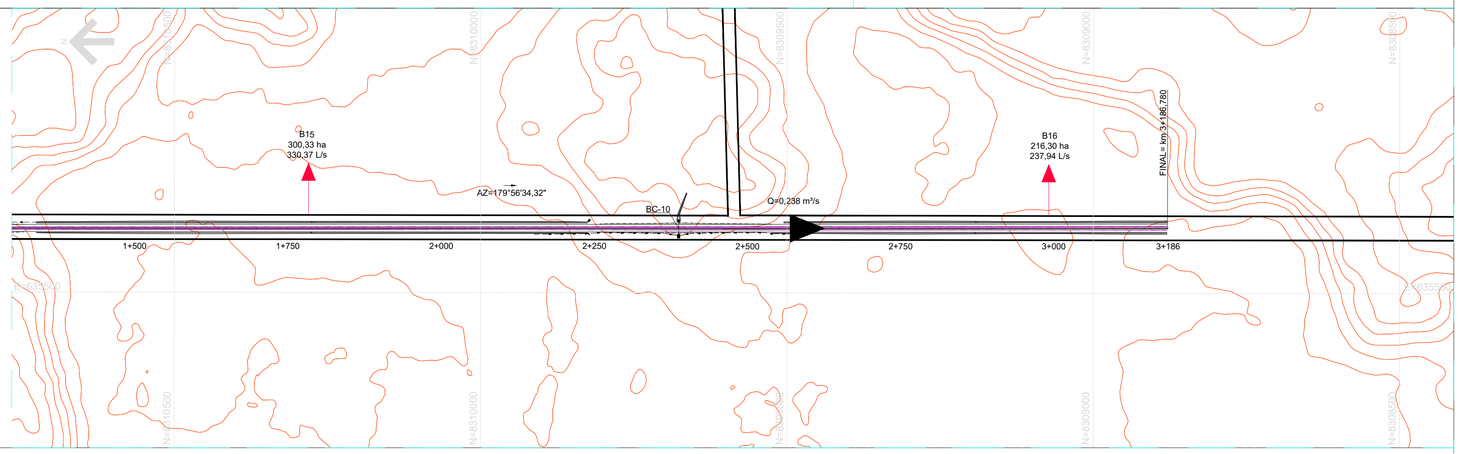
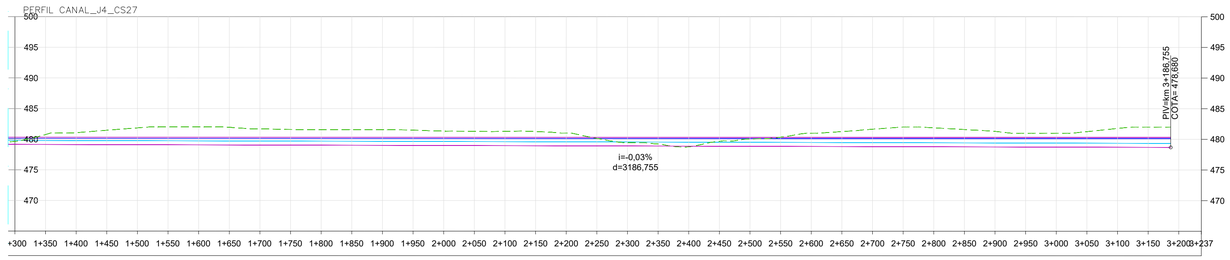
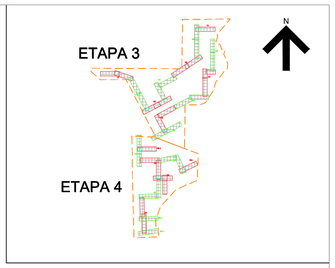










MAPA CHAVE

LEGENDA:

PLANTA:

- Canal Adutor
- Curvas de Nível Mestra
- Curvas de Nível Intermediárias
- Cursos d'Água
- Estradas
- Estrutura de Controle
- Valeta de Proteção de Corte e de Aterro
- Sarjeta Triangular de Corte
- Dissipador de Energia
- Bueiro Simples Tubular de Concreto
- Boca Simples
- Bacia de Captação

PERFIL:

- Terreno Natural
- Topo da Berma
- Nível D'água Dinâmico
- Nível D'água Estático
- Fundo do Canal
- Estrutura de Controle

NOTAS:

01 - MEDIDAS EM METROS, EXETO INDICAÇÃO CONTRÁRIA;
02 - SISTEMA DE COORDENADAS: DATUM SIRGAS 2000, UTM-23S;
03 - TERRENO OBTIDO DO LEVANTAMENTO TOPOGRÁFICO;

Revisão	Data	Descrição	Elab.	Verif.	Aprov.	Aut.
-	-	-	-	-	-	-
-	-	-	-	-	-	-
-	-	-	-	-	-	-
-	-	-	-	-	-	-
00	21/11/25	EMISSÃO INICIAL	JOP	AHL	EDK	-

FUNDO DE DESENVOLVIMENTO DA INFRAESTRUTURA REGIONAL SUSTENTÁVEL - FDIRS

ESTRUTURAÇÃO DE PROJETO DE CONCESSÃO DO PERÍMETRO IRRIGADO DO JAÍBA (ETAPAS 3 E 4)

ANTEPROJETO

SISTEMA ADUTOR
PLANTA E PERFIL - ETAPA 4
FOLHA 06

Finalidade de Emissão: 1 Para Informação | 2 Para Comentários | 3 Para Aprovação | 4 Para Execução | 5 Como Construído | 6 Para Utilização | 7 Para Providências

Moysés & Pires Consultoria de Engenharia | ENGECORPS Grupo FIPSA | Plena Consultoria e Projetos

Data: 21/11/25
Elaboração:
Verificação:
Escala: 1:500 / 1:500 (H:V)
Aprovação: - / -
Autorização: - / -
Referência:
Revisão: 00
Desenho nº: J4-DS-HI-005